Coquill'App

Application mobile d'aide à la pêche à pied

Sommaire

Rappel du sujet **3**
Exploration **4**
1. Existant / Benchmarking 4
2. Recherche documentaire 5
3. Usagers - persona 8
4. User Journey Map - Pain points 9
Idéation **10**
5. Synthèse et problématique design 10
6. Liste des fonctionnalités & hiérarchisation de ces fonctionnalités 11
SCAMPER 13
Génération - Evaluation **14**
7. Wireframe 14
8. Test : System Usability Scale 17
Conclusion **18**
Annexes **19**

Rappel du sujet

Dans le cadre du projet de la Ressource R3.03 - Design d'expérience, nous avons réalisé le maquettage, défini les fonctionnalités ainsi que les wireframes d'une application mobile destinée à accompagner la pêche à pied pour les pêcheurs occasionnels et les touristes.

Après avoir analysé les solutions existantes et mené une recherche documentaire sur cette pratique et ses enjeux, nous avons pris en compte les besoins des utilisateurs à l'aide d'un persona et d'une User Journey Map, ce qui nous a permis de définir une problématique de design. Dans cette approche, nous avons ensuite élaboré une liste de fonctionnalités enrichie grâce à la méthode SCAMPER, ainsi que les wireframes de l'ensemble des écrans de l'application.

Nous avons enfin évalué la qualité de son ergonomie via le System Usability Scale et identifié des pistes d'amélioration, développées plus en détail par la suite.

Exploration

1. Existant / Benchmarking

Voici des concurrents qui sont sur le même marché que nous, ainsi que leurs services / produits proposés dans leur application.

FishFriender	https://www.fishfriender.com/Lapplication-mobile-des-pecheurs-a-pied?_locale=fr	L'application vous permet d'entretenir un véritable carnet de pêche numérique. Vous avez la possibilité de conserver un historique détaillé de toutes vos prises. Grâce à la fonction "prise rapide", l'application se charge de récupérer l'ensemble des informations climatiques relatives à votre prise.
FishAngler	https://www.fishangler.com/fishing-map?lat=26.0817057&lng=-80.1707762&zoom=12	Avec FishAngler, vous pouvez découvrir de nouveaux spots de pêche, obtenir des prévisions de pêche en temps réel et trouver les meilleurs moments pour attraper du poisson
Fishbrain	https://fishbrain.com/	Fishbrain fournit les cartes et les outils nécessaires pour améliorer vos compétences de pêche . Fishbrain est le moyen le plus rapide et le plus simple de trouver des lieux de pêche. Explorez des milliers de zones de pêche et voyez précisément où les poissons sont pêchés grâce à la carte Fishbrain.
Fishsurfing	https://www.fishsurfing.com/fr/	Fishsurfing est un réseau social dédié à la pêche, disponible sur mobile et ordinateur. Il permet de suivre d'autres pêcheurs, partager photos, vidéos et conseils, et s'inspirer de leurs expériences. L'application propose aussi une carte interactive indiquant spots de pêche, hébergements, magasins et guides locaux pour faciliter l'organisation de vos sorties.

2. Recherche documentaire

Voici les ressources documentaires que nous avons trouvé, et qui nous aident à l'utilité des informations à mettre dans notre application.

THÉMATIQUE	URL	COMMENTAIRE	UTILITÉ
SÉCURITÉ			
Article de loi	https://www.dirm.nord-atlantique-manche-ouest.developpement-durable.gouv.fr/peche-a-pied-reglementation-securite-et-a436	**réglementation de la pêche à pieds**	
Site interactif	https://www.pecheapied-loisir.fr/bonnes-pratiques/	**regroupe plein d'information sur le domaine**	
Article	https://www.snsm.org/conseils/conseils-plage/tout-savoir-sur-la-peche-pied	**Conseils sécurité + réglementation**	
Article de loi	https://www.dirm.nord-atlantique-manche-ouest.developpement-durable.gouv.fr/pecher-en-securite-lors-des-grandes-marees-a595	**Règles spécifiques grandes marées**	
Article	https://www.ouest-france.fr/bretagne/peche-pied-respecter-la-reglementation-3733314	**Rappel des règles à respecter**	
Article	https://www.welcomecamping.com/4-precieux-conseils-pour-sinitier-a-la-peche-a-pied	**Conseils simples pour débutants**	

EQUIPEMENT			
Article	https://www.snsm.org/conseils/conseils-plage/tout-savoir-sur-la-peche-pied	**Infos générales, inclut équipement**	
Article	https://atelier-retour-de-peche.com/les-equipements-pour-la-peche-a-pied	**Détail du matériel nécessaire**	
Blog	https://conseilsport.decathlon.fr/decouvrir-la-peche-a-pied	**Conseils pratiques et équipements**	
TECHNIQUE			
Site interactif	https://www.pecheapied-loisir.fr/bonnes-pratiques/	**Regroupe plein d'information sur le domaine**	
Article	https://www.nootica.fr/webzine/pratiquer-peche-a-pied.html		
Site interactif	https://www.tourisme-granville-terre-mer.com/decouvrir/les-plus-grandes-marees-d-europe/peche-a-pied-responsable		
Article	https://cotepeche.fr/une-peche-a-pied-vraiment-pas-comme-les-autres		
FRUITS DE MER			
Guide pratique	https://pecheapied.net/	**liste des fruits de mer**	

Article	**https://www.snsm.org/conseils/conseils-plage/tout-savoir-sur-la-peche-pied**	**Liste et description des espèces à pêcher**	
LIEUX			
Carte en ligne	**https://maree.info/**	**Annuaire des marées**	
RETOUR D'EXPÉRIENCE			
Reportage	**https://www.youtube.com/watch?v=NsZs_mJuo9Y&ab_channel=ReportageExpress**	**Témoignages et immersion**	
CONTEXTE ET CHIFFRES			
Encyclopédie	**https://fr.wikipedia.org/wiki/P%C3%AAche_%C3%A0_pied**	**Origines, pratiques selon zones, population pratiquante, impact économique**	

3. Usagers - persona

Voici le Persona que nous avons réalisé en tant qu'utilisateur type.

Gilbert DESBORDES

D'après C. Lallemand & G. Gonier

Gilbert DESBORDES
67 ans
Marié
Vit à Dijon

Ancien botaniste

À la retraite, j'ai découvert en Bretagne la pêche à pied, qui est devenue une vraie passion. Cette activité me permet d'explorer la richesse des coquillages et des mollusques tout en profitant de la nature et de moments simples avec ma femme.

Vivant actuellement à Dijon et, n'ayant pas grandi dans l'univers de la mer, j'ai découvert tardivement ses richesses. Marié depuis de nombreuses années, je profite de ma retraite pour voyager avec ma femme et partager des moments simples ensemble. C'est lors de vacances en Bretagne que je suis tombé amoureux de la pêche à pied : une activité qui m'a ouvert à la diversité des coquillages et des mollusques, et qui me permet aujourd'hui de concilier découverte de la nature et plaisir du grand air.

Depuis que j'ai découvert la pêche à pied lors de vacances en Bretagne, je pratique régulièrement cette activité qui me passionne.
J'ai appris à :

- reconnaître les différentes espèces de coquillages et mollusques
- identifier les meilleurs endroits pour les trouver
- maîtriser les techniques de récolte tout en respectant l'environnement et les règles locales.

Patient et attentif, j'apprécie autant l'observation de la faune que la satisfaction de ma pêche

Volonté / Motivation :

- *Envie de découvrir de nouvelles espèces et de nouveaux sites.*
- *Souhait de mieux identifier et comprendre la flore marine.*
- *Recherche d'un outil pratique pour planifier ses sorties et connaître les périodes ou zones de pêche autorisées.*

Freins / Obstacles :

- *Peu à l'aise avec la technologie*
- *Préférence pour l'expérience directe de la nature plutôt que le suivi numérique.*
- *Crainte que l'application ne soit pas suffisamment à jour concernant les espèces ou les zones de pêche.*

Gilbert est peu à l'aise avec le numérique et préfère les expériences concrètes. Il utilise les outils numériques de manière simple et reste méfiant face aux informations non vérifiées en ligne.

4. User Journey Map - Pain points

	Avant				Pendant		Après
Penser	S'informer sur les espèces à pêcher	Trouver un lieu de pêche	S'informer sur la marée - la météo - le coefficient	Regarder la réglementation et les règles de sécurité	Être dans les réglementations, respecter les tailles et quotas	Regarder si la marée ne monte pas trop vite	Nettoyer les coquillages pour éviter les risques
Faire	S'informer et regarder sur internet, ou dans un livre	Regarder sur internet les différents lieux où la pêche est autorisée	Regarder sur internet	S'informer sur des sites internet	Vérifier la tailler et trier les prises	Observer le sol et l'avancé de l'eau	Laver les coquillages, et regarder sur internet ou dans un livre si besoin de conseils
Peurs	Ne pas trouver d'espèces à pêcher sur le lieu de pêche	L'endroit est trop éloigné ou la pêche est interdite, ne pas savoir exactement où aller	La météo est mauvaise et il est impossible de pêcher	Ne pas être dans les règles	Être contrôlé et ne pas être dans les règles	Se faire surprendre par la marée montante et rester bloqué	Risque sanitaire ou de tomber malade (produit pas frais)
Ressenti	Curiosité	Motivation, envie de passer un bon moment	Excitation, hâte d'y aller, ou déçu si mauvais temps	Rassurer	Bien-être dans la nature, se sentir dans les règles et rassurer	Stress léger	Satisfaction d'avoir péché sois même

Idéation

5. Synthèse et problématique design

La pêche à pied attire de nombreux curieux, mais cette activité reste complexe pour les débutants, qui ne savent pas toujours où aller, comment reconnaître les espèces et comment pratiquer en toute sécurité. Ce manque d'accompagnement peut rendre l'expérience frustrante ou risquée.

Notre application répond à ce problème en offrant un support simple et accessible qui guide l'utilisateur avant et pendant sa sortie. Elle combine information, sécurité et pédagogie, tout en proposant un carnet de suivi personnel qui permet de garder une trace de ses découvertes. L'objectif est de rendre la pêche à pied plus sûre, plus intuitive et plus enrichissante, aussi bien pour les touristes que pour les pratiquants occasionnels.

6. Liste des fonctionnalités & hiérarchisation de ces fonctionnalités

1. Écran d’accueil / Connexion

- Logo + nom de l’application
- Court texte d’intro : "Découvrez les meilleurs spots et règles pour la pêche à pied."
- Boutons : Se connecter, Créer un compte, Continuer en invité

2. Accueil

- Barre de recherche : "Rechercher un spot ou une espèce…"
- Onglets principaux (menu en bas) : Accueil, Spots, Marées et Espèces, Carnet de pêche, Profil

3. Spots de pêche

- Carte interactive avec géolocalisation
- Filtres : Distance (près de moi), type de coquillage/poisson, accessibilité (famille, confirmé), marée (haute ou basse)
- Liste avec photos + infos rapides : nom du spot, distance, marée favorable

4. Fiche Spot (détail)

- Photo du lieu
- Coordonnées GPS + bouton "Y aller" (lien Maps)
- Infos pratiques : meilleure période de pêche, espèces présentes, réglementation locale (quantité max, taille minimale)
- Bouton "Ajouter à mes favoris"

5. Espèces

- Liste illustrée (ex : palourde, bigorneau, huître, crabe…)
- Filtres : comestible / protégé / facile à trouver
- Fiche espèce : photo, taille minimale autorisée, limite de prélèvement, recettes ou astuces

6. Marées

- Calendrier des marées (jour + heure basse/haute)
- Alertes personnalisées ("Préviens-moi 2h avant la marée basse")
- Indicateur météo/mers (vent, pluie…)

7. Carnet de pêche + détails statistiques

- Journal personnel avec photos
- Saisie rapide : espèce + quantité + lieu + date
- Statistiques : total ramassé, espèces les plus fréquentes, progression

8. Profil

- Infos utilisateur (nom, photo de profil)
- Mes spots favoris
- Mes carnets sauvegardés
- Paramètres

SCAMPER

Afin d’enrichir et d’améliorer notre concept, nous avons appliqué la méthode **SCAMPER**. Cette approche nous a permis de repenser certains problèmes identifiés dans le parcours utilisateur et de les transformer en fonctionnalités concrètes et utiles pour notre application. Voici quelques exemples issus de cette réflexion :

- Combiner: la météo est mauvaise et il est impossible de pêcher + se faire surprendre par la marée montante et rester bloqué
=> Fonctionnalité : recense la météo et le niveau de la marée en fonction de la position ou d’un lieu donné par l’utilisateur

- Combiner: ne pas trouver d'espèces à pêcher sur le lieu de pêche + l'endroit est trop éloigné ou la pêche est interdite, ne pas savoir exactement où aller
=> Fonctionnalité : l’application contient une carte qui indique les endroits où l’on peut pêcher

- Substituer : ne pas être dans les règles + être contrôlé et ne pas être dans les règles
=> Fonctionnalité : permet à l’utilisateur d’ajouter ces informations personnelles (carte d’identité, permis de pêche…)

- Adapter : risque sanitaire ou de tomber malade (produit pas frais)
=> Fonctionnalité : l’application indique à l’utilisateur comment cuisiner chaque espèces pour ne pas tomber malades et comment les conserver (comparable aux dates de péremption et aux méthodes de conservations en supermarché)

Génération - Evaluation

7. Wireframe

Écran d’accueil / Connexion

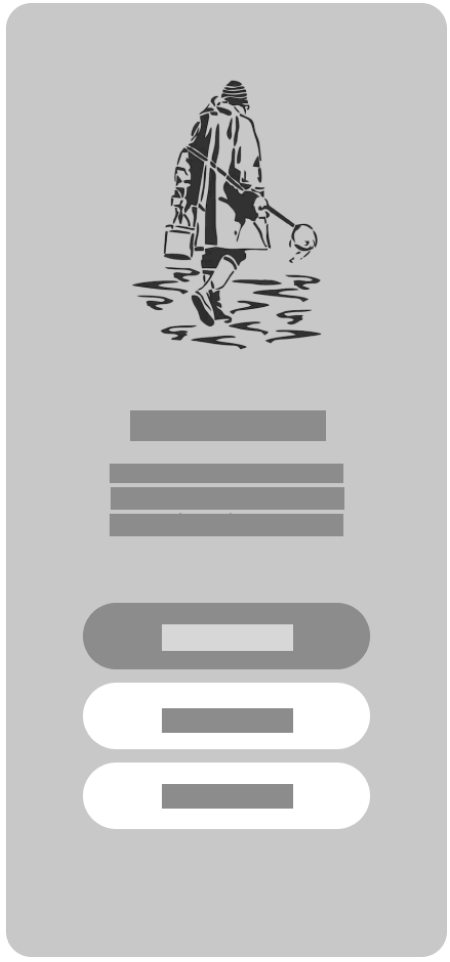

Accueil



Spots de pêche



Fiche spot (détail)

Espèces



Marées



Carnet de pêche

Détails statistiques

Profil

8. Test : System Usability Scale

Pour évaluer l'ergonomie de notre application, nous avons utilisé la méthode **System Usability Scale (SUS)**.
Nous avons présenté nos wireframes aux testeurs et leur avons demandé de réaliser quelques actions simples (ex. : consulter la météo des marées, accéder à son profil).
À la fin, ils ont rempli le questionnaire SUS (10 affirmations, échelle de 1 = Pas du tout d'accord à 5 = Tout à fait d'accord).

Résultats

Nous avons testé notre maquette auprès de **6 participants**.
Voici leurs scores SUS individuels (sur 100) :**Moyenne : 74 / 100**

Participant	Score SUS
Participant 1	75
Participant 2	68
Participant 3	82
Participant 4	70
Participant 5	77
Participant 6	73

Interprétation

Un score de 74 est supérieur à la moyenne (68). Cela signifie que notre application présente déjà une bonne utilisabilité, même au stade de wireframe.

Améliorations identifiées

- Rendre certaines icônes plus compréhensibles en ajoutant des labels.
- Simplifier la navigation entre les écrans “calendrier” et “sécurité”.
- Mettre davantage en valeur les fonctions principales (météo, spots).

Conclusion

Ce projet nous a permis de concevoir une application mobile destinée à accompagner les pêcheurs occasionnels et les touristes dans la pratique de la pêche à pied. L'évaluation réalisée avec le System Usability Scale a montré que, même au stade des wireframes, l'application obtient un score supérieur à la moyenne (74/100), ce qui traduit une bonne ergonomie générale. Toutefois, certains points méritent d'être surveillés, comme la clarté des icônes, la fluidité de la navigation entre les sections et la mise en valeur des fonctionnalités principales telles que la météo, les marées et la localisation des zones de pêche.

Notre proposition se distingue des solutions existantes car elle ne se limite pas à un simple carnet de pêche ou à une plateforme sociale. Elle combine sécurité, pédagogie et convivialité, tout en plaçant l'expérience utilisateur au centre, grâce à des informations pratiques directement accessibles sur le terrain. Elle répond également aux besoins identifiés dans nos personas et notre User Journey Map, en réduisant les peurs principales des utilisateurs, qu'il s'agisse du respect des règles, des risques liés aux marées ou du manque d'informations fiables.

En définitive, ce projet apporte une solution innovante et centrée sur l'utilisateur. L'application améliore l'expérience des pêcheurs novices comme occasionnels et favorise une pratique plus responsable et sécurisée. Avec les ajustements ergonomiques identifiés lors du test SUS, elle possède le potentiel de devenir un outil de référence pour la pêche à pied.

Annexes

User journey map / Recherche documentaire
https://docs.google.com/spreadsheets/d/1vUQLlGYHoDZtbQTIhKdbNuws7Ki36q2xZ1FbGWIBk0Q/edit?usp=sharing

Lien Figma
https://www.figma.com/design/2JyS3qxNLqvZ76HOd2YSxl/Untitled?node-id=17-271&t=fyluisSosMmtTpLw-1